GERENCIAMENTO DOS RECURSOS HÍDRICOS

SITUAÇÃO ATUAL DOS AÇUDES

BOLETIM INFORMATIVO

FORTALEZA - CE
06/08/25 - 11:09h

COMPANHIA DE GESTÃO DOS RECURSOS HÍDRICOS
DIRETORIA DE OPERAÇÕES
GERÊNCIA DE MONITORAMENTO QUALITATIVO E QUANTITATIVO

CEARÁ
GOVERNO DO ESTADO
SECRETARIA DOS RECURSOS HÍDRICOS

VOLUME RELATIVO DO APORTE NO ANO - 06/08/2025

CONVÊNIOS: COGERH / DNOCS /

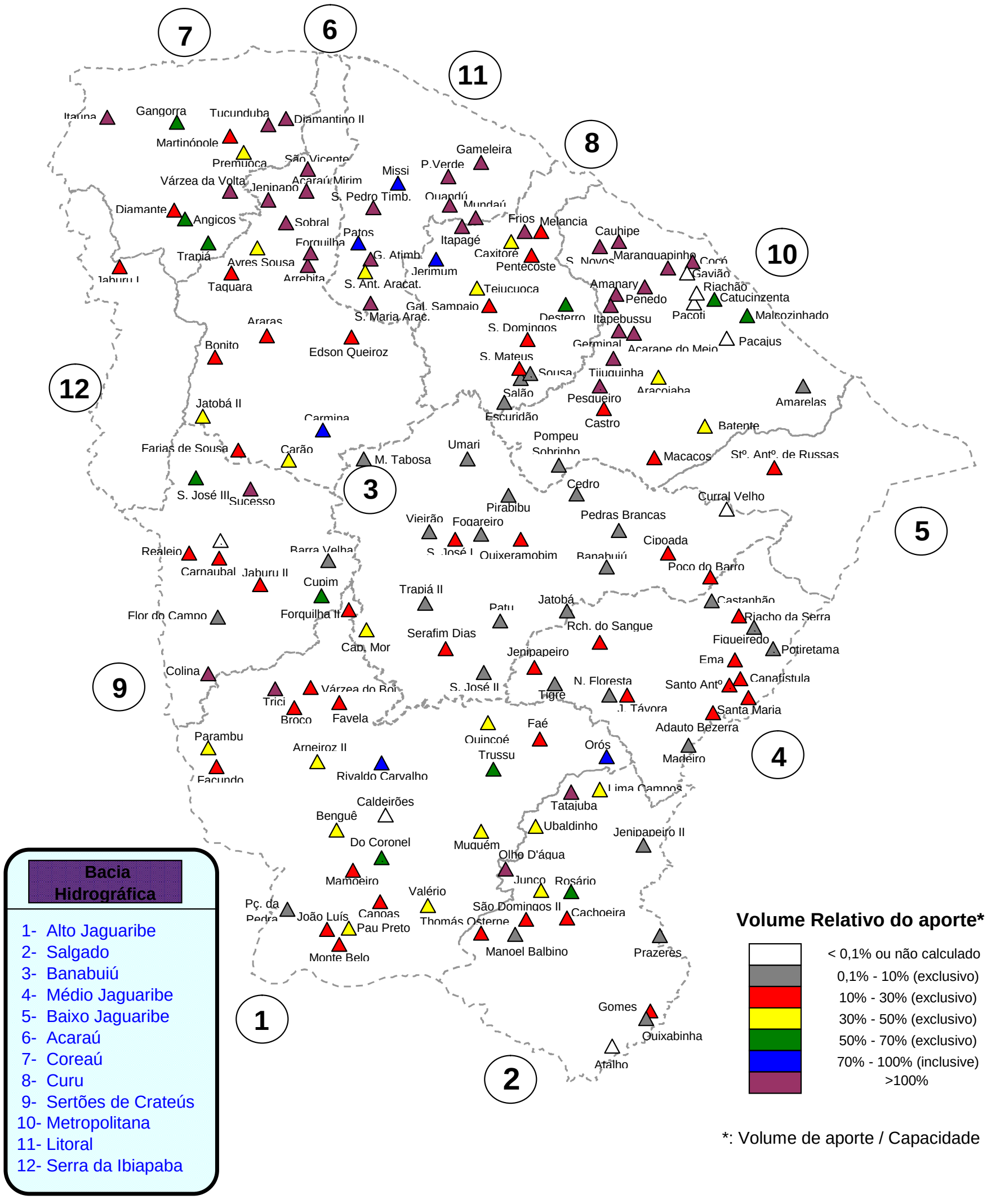

Bacia Hidrográfica

1- Alto Jaguaribe
2- Salgado
3- Banabuiú
4- Médio Jaguaribe
5- Baixo Jaguaribe
6- Acaraú
7- Coreaú
8- Curu
9- Sertões de Crateús
10- Metropolitana
11- Litoral
12- Serra da Ibiapaba

Volume Relativo do aporte*

- < 0,1% ou não calculado
- 0,1% - 10% (exclusivo)
- 10% - 30% (exclusivo)
- 30% - 50% (exclusivo)
- 50% - 70% (exclusivo)
- 70% - 100% (inclusive)
- >100%

*: Volume de aporte / Capacidade

COMPANHIA DE GESTÃO DOS RECURSOS HÍDRICOS
DIRETORIA DE OPERAÇÕES
GERÊNCIA DE MONITORAMENTO QUALITATIVO E QUANTITATIVO

CEARÁ GOVERNO DO ESTADO
SECRETARIA DOS RECURSOS HÍDRICOS

SITUAÇÃO ATUAL DOS AÇUDES - 06/08/2025

CONVÊNIOS: COGERH / DNOCS /

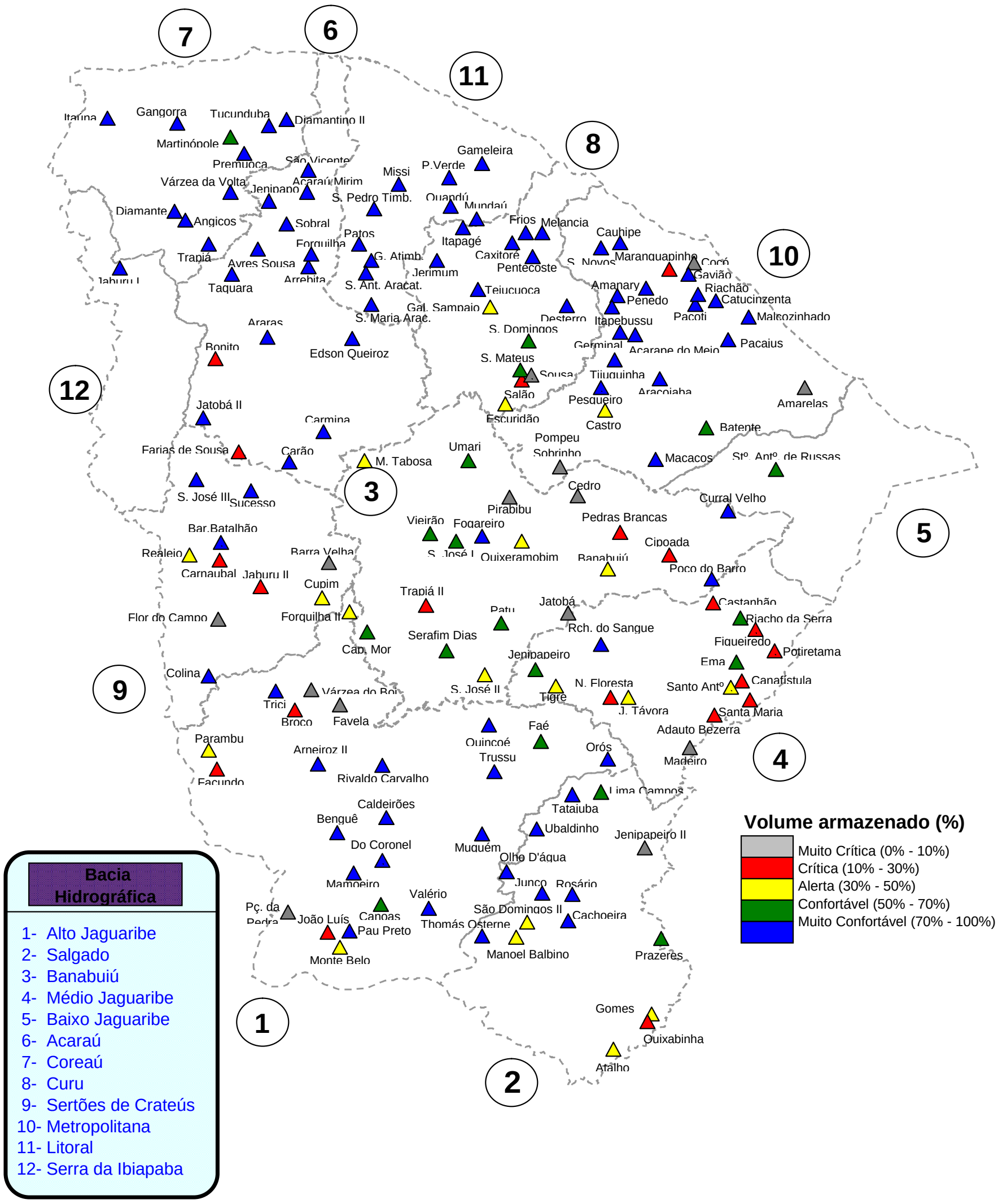

Bacia Hidrográfica

1- Alto Jaguaribe
2- Salgado
3- Banabuiú
4- Médio Jaguaribe
5- Baixo Jaguaribe
6- Acaraú
7- Coreaú
8- Curu
9- Sertões de Crateús
10- Metropolitana
11- Litoral
12- Serra da Ibiapaba

COMPANHIA DE GESTÃO DOS RECURSOS HÍDRICOS
DIRETORIA DE OPERAÇÕES
GERÊNCIA DE MONITORAMENTO QUALITATIVO E QUANTITATIVO

Volume d´água armazenado por bacia hidrográfica neste mês em relação aos anos anteriores

CONVÊNIOS: COGERH / DNOCS / FUNCEME

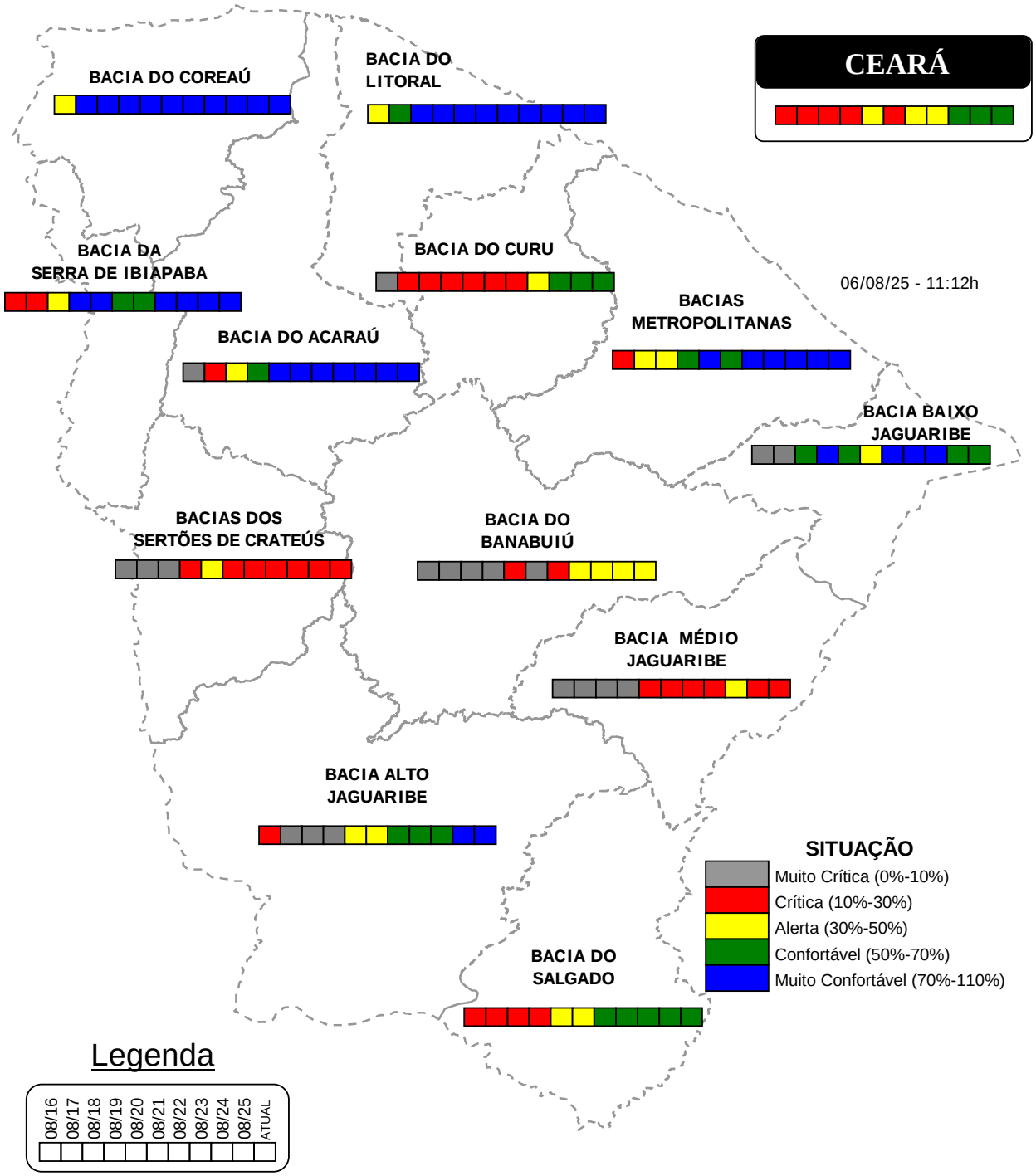

COMPANHIA DE GESTÃO DOS RECURSOS HÍDRICOS
DIRETORIA DE OPERAÇÕES
GERÊNCIA DE MONITORAMENTO QUALITATIVO E QUANTITATIVO

Volume d´água armazenado por bacia hidrográfica

CONVÊNIOS: COGERH / DNOCS /

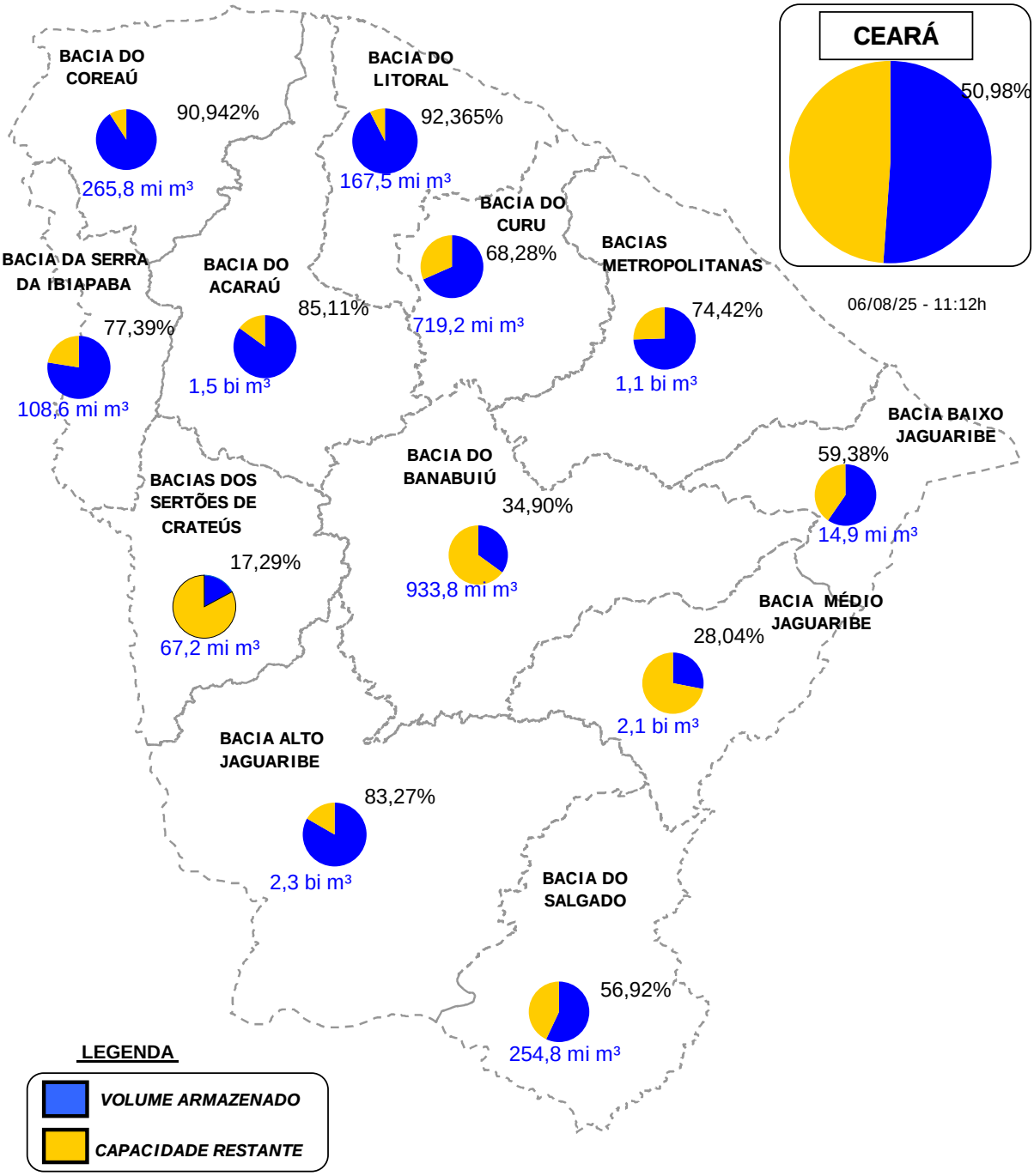

COMPANHIA DE GESTÃO DOS RECURSOS HÍDRICOS
DIRETORIA DE OPERAÇÕES
GERÊNCIA DE MONITORAMENTO QUALITATIVO E QUANTITATIVO

Evolução do volume de água armazenado por bacia hidrográfica: final da estação chuvosa, início do ano e situação atual

CONVÊNIOS: COGERH / DNOCS / FUNCEME

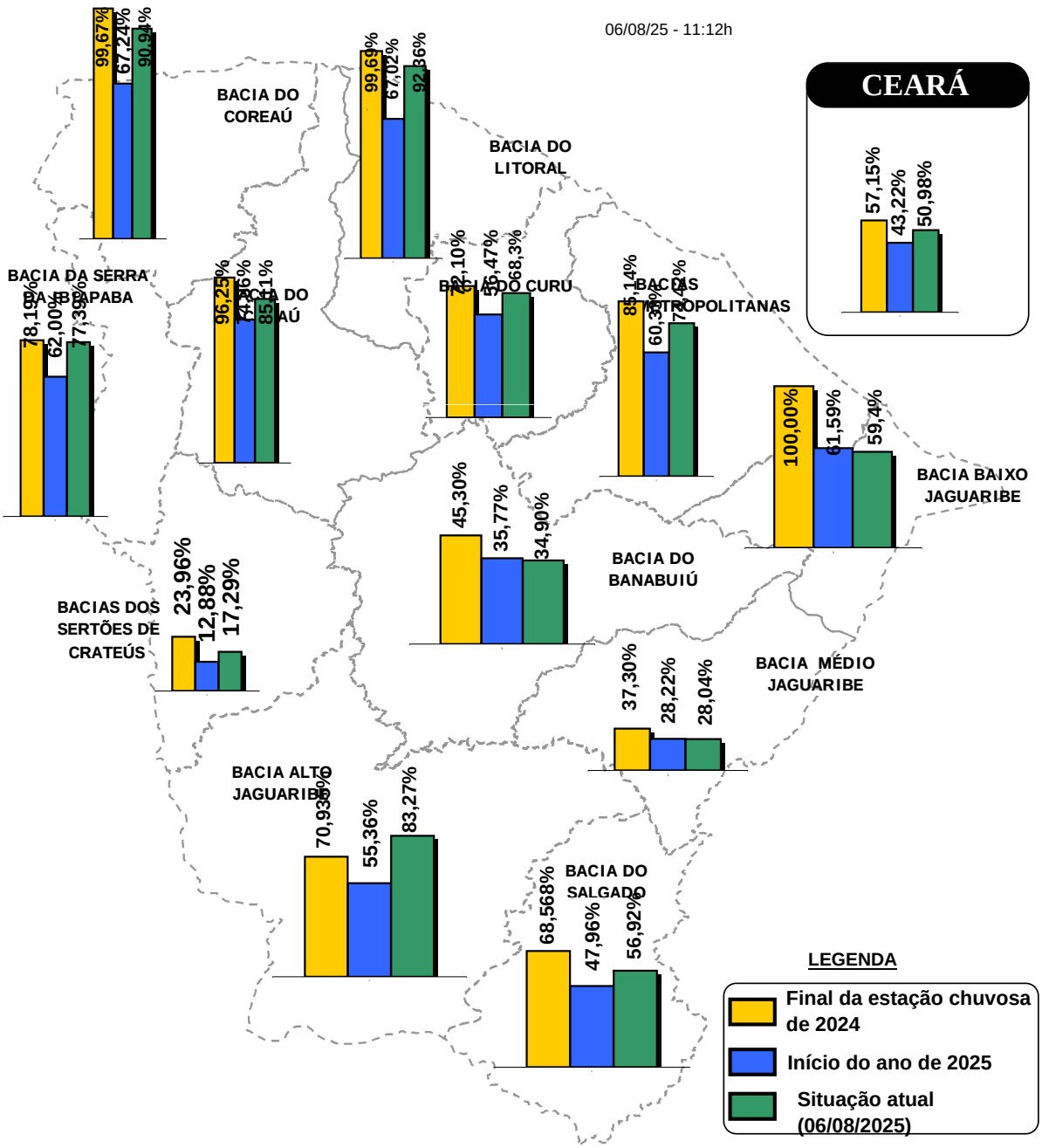

COMPANHIA DE GESTÃO DOS RECURSOS HÍDRICOS
DIRETORIA DE OPERAÇÕES
GERÊNCIA DE MONITORAMENTO QUALITATIVO E QUANTITATIVO

Evolução dos maiores volumes armazenados a cada ano

CONVÊNIOS: COGERH / DNOCS / FUNCEME

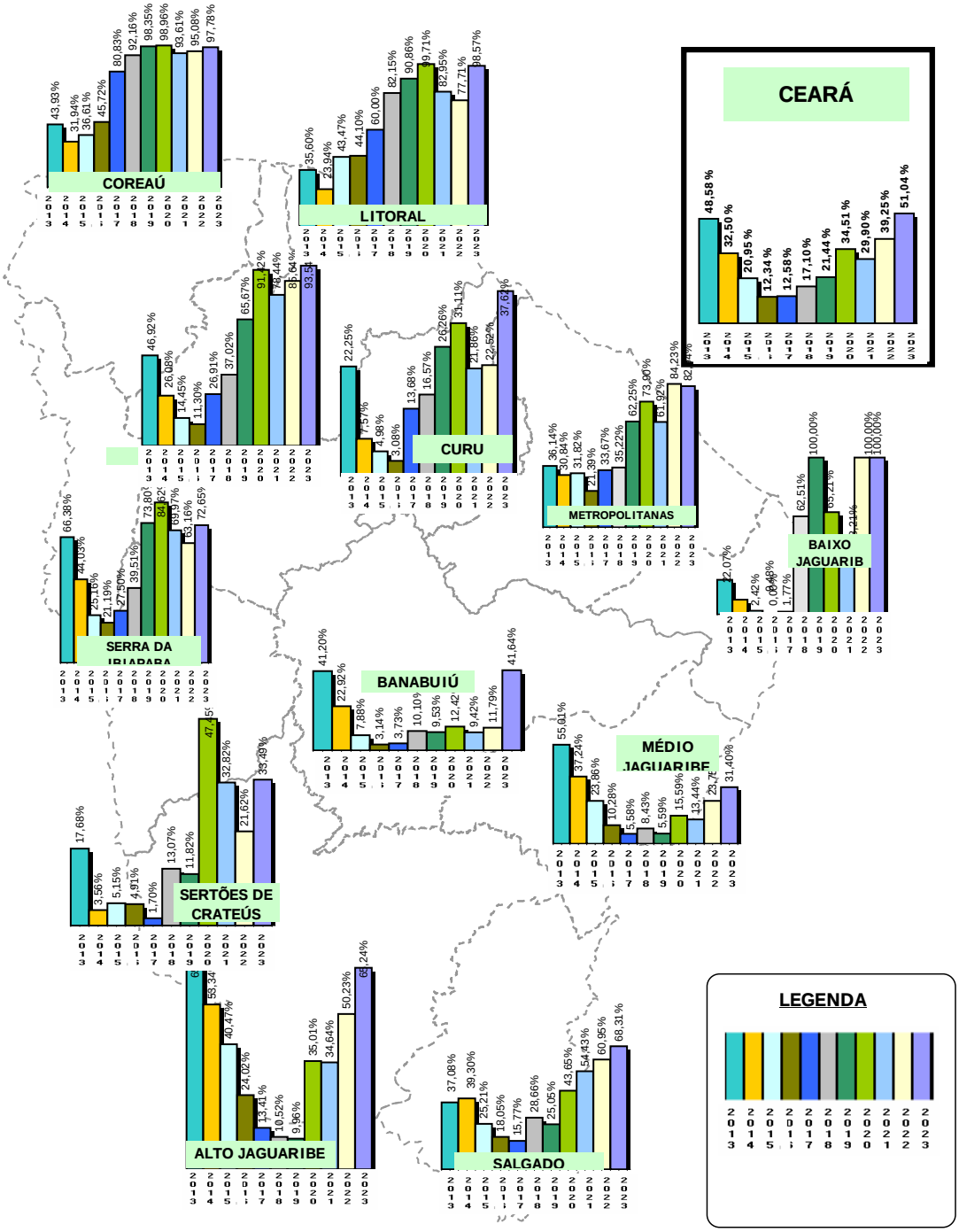

COMPANHIA DE GESTÃO DOS RECURSOS HÍDRICOS
DIRETORIA DE OPERAÇÕES
GERÊNCIA DE MONITORAMENTO QUALITATIVO E QUANTITATIVO

CEARÁ GOVERNO DO ESTADO
SECRETARIA DOS RECURSOS HÍDRICOS

PROGRAMA DE GERENCIAMENTO DAS ÁGUAS TERRITORIAIS

CONVÊNIO: COGERH / DNOCS

QUADRO RESUMO

06/08/25 - 11:12h

Bacia	Capacidade (m³)	Volume Armazenado (m³)				Volume Armazenado (%)				Aporte
		Ano passado (06/08/2024)	Final da estação chuvosa passada (01/06/2024)	Início do ano (01/01/2025)	Atual (06/08/2025)	Ano passado (06/08/2024)	Final da estação chuvosa passada (01/06/2024)	Início do ano (01/01/2025)	Atual (06/08/2025)	
Sertões de Crateús	388.481.877	80.985.577	93.096.046	50.021.433	67.172.890	20,85%	23,96%	12,88%	17,29%	389,181 milhões de m³
Médio Jaguaribe	7.372.889.685	2.604.378.552	2.750.025.034	2.080.289.704	2.067.209.337	35,32%	37,30%	28,22%	28,04%	431,279 milhões de m³
Banabuiú	2.675.859.299	1.179.277.651	1.212.182.030	957.188.891	933.845.413	44,07%	45,30%	35,77%	34,90%	138,916 milhões de m³
Salgado	447.661.833	282.315.519	306.952.288	214.712.226	254.820.572	63,06%	68,57%	47,96%	56,92%	145,965 milhões de m³
Baixo Jaguaribe	25.050.893	23.153.017	25.050.893	15.429.486	14.874.420	92,42%	100,00%	61,59%	59,38%	7,333 milhões de m³
Curu	1.053.366.104	724.759.886	759.512.399	594.845.553	719.213.727	68,80%	72,10%	56,47%	68,28%	450,353 milhões de m³
Metropolitanas	1.459.836.188	1.189.533.583	1.242.975.662	880.648.259	1.086.338.695	81,48%	85,14%	60,33%	74,42%	1,076 bilhão de m³
Serra da Ibiapaba	140.325.089	108.225.123	109.715.606	86.998.110	108.597.744	77,12%	78,19%	62,00%	77,39%	31,074 milhões de m³
Alto Jaguaribe	2.738.820.329	1.838.818.652	1.942.793.668	1.516.310.331	2.280.654.021	67,14%	70,94%	55,36%	83,27%	2,046 bilhões de m³
Acaraú	1.720.295.864	1.577.857.462	1.655.835.047	1.279.154.201	1.464.221.177	91,72%	96,25%	74,36%	85,11%	775,964 milhões de m³
Coreaú	292.238.934	277.168.041	291.288.551	196.514.571	265.769.294	94,84%	99,67%	67,24%	90,94%	529,125 milhões de m³
Litoral	181.351.402	168.417.035	180.787.202	121.544.883	167.505.127	92,87%	99,69%	67,02%	92,36%	396,409 milhões de m³
TOTAL	**18.496.177.497**	**10.054.890.098**	**10.570.214.427**	**7.993.657.648**	**9.430.222.418**	**54,36%**	**57,15%**	**43,22%**	**50,98%**	**6,418 bilhões de m³**

COMPANHIA DE GESTÃO DOS RECURSOS HÍDRICOS
DIRETORIA DE OPERAÇÕES
GERÊNCIA DE MONITORAMENTO QUANTITATIVO E QUALITATIVO

CEARÁ GOVERNO DO ESTADO
SECRETARIA DOS RECURSOS HÍDRICOS

PROGRAMA DE GERENCIAMENTO DAS ÁGUAS TERRITORIAIS

CONVÊNIO: COGERH / DNOCS

Evolução dos maiores volumes armazenados a cada ano

	2004		2005		2006		2007		2008		2009		2010	
	m³	%	m³	%	m³	%	m³	%	m³	%	m³	%	m³	%
Alto Jaguaribe	2.569.541.901	99,9%	2.126.346.631	82,7%	1.991.060.648	71,3%	2.020.207.793	72,3%	2.690.322.988	96,3%	2.753.679.422	98,57%	2.359.090.734	84,45%
Salgado	409.133.103	91,5%	310.452.116	69,4%	332.314.403	74,3%	276.858.623	61,9%	417.073.904	93,3%	415.867.232	92,99%	318.179.581	71,25%
Banabuiú	2.301.255.079	83,5%	1.897.170.117	68,8%	1.601.842.933	58,1%	1.275.392.012	46,3%	1.879.592.112	67,9%	2.525.063.265	91,22%	2.131.257.919	76,99%
Médio Jaguaribe	5.151.074.868	75,2%	4.541.551.401	66,3%	4.759.397.385	69,4%	4.261.246.090	62,1%	6.168.233.914	89,9%	6.712.525.715	97,84%	5.414.490.672	78,92%
Baixo Jaguaribe	23.999.990	100,0%	17.499.092	72,9%	23.999.990	100,0%	15.395.000	64,1%	18.455.502	76,9%	23.999.990	100,00%	21.452.180	89,38%
Acaraú	1.436.267.760	99,5%	1.152.116.041	79,8%	1.121.095.306	77,7%	915.934.531	63,4%	1.398.067.597	96,8%	1.443.767.000	100,00%	1.162.449.268	80,52%
Coreaú	281.806.708	94,9%	241.229.655	81,2%	263.135.938	88,6%	269.525.898	90,7%	281.257.901	94,7%	297.090.000	100,00%	210.863.619	70,98%
Curu	1.043.507.659	97,7%	801.194.523	75,0%	852.576.350	79,8%	617.217.477	57,8%	746.964.975	69,9%	1.068.355.046	100,00%	861.320.276	80,62%
Sertões de Crateús	656.464.524	97,4%	402.917.200	85,4%	307.613.600	65,2%	290.157.000	61,5%	457.174.200	96,9%	471.800.000	100,00%	359.181.340	76,13%
Metropolitanas	1.247.587.642	94,1%	957.424.798	72,2%	1.015.763.009	76,6%	880.906.472	66,5%	971.081.710	72,2%	1.318.767.509	97,36%	1.070.674.028	79,05%
Litoral	98.290.006	100,0%	66.530.439	67,7%	81.929.265	83,4%	61.972.387	63,1%	95.421.865	97,1%	98.290.006	100,00%	74.313.332	75,61%
Serra da Ibiapaba			133.477.908	97,6%	131.700.026	96,3%	126.229.620	92,3%	136.760.152	100,0%	136.760.152	100,00%	128.349.403	93,85%
Ceará	**15.020.861.404**	**85,6%**	**12.647.909.921**	**71,0%**	**12.482.428.853**	**70,5%**	**11.011.042.903**	**62,0%**	**15.260.406.820**	**85,8%**	**17.265.965.337**	**96,13%**	**14.111.622.352**	**79,38%**
LEGENDA	**15.020.861.404**	**85,6%**	**12.647.909.921**	**71,0%**	**12.482.428.853**	**70,5%**	**11.011.042.903**	**62,0%**	**15.260.406.820**	**85,8%**	**17.265.965.337**	**96,13%**	**14.111.622.352**	**79,38%**

	2011		2012		2013		2014		2015		2016		2017	
	m³	%	m³	%	m³	%	m³	%	m³	%	m³	%	m³	%
Alto Jaguaribe	2.694.664.051	96,46%	2.298.726.117	88,53%	1.830.575.144	65,31%	1.511.480.537	53,34%	1.125.894.016	40,47%	667.688.023	24,02%	372.683.031	13,41%
Salgado	357.927.542	79,79%	297.990.340	60,56%	182.455.115	37,08%	193.378.803	39,30%	114.027.855	25,21%	82.030.549	18,05%	71.307.105	15,77%
Banabuiú	2.286.576.846	81,57%	1.927.141.387	68,75%	1.154.883.274	41,20%	642.473.899	22,92%	217.543.239	7,88%	86.912.723	3,14%	102.934.881	3,73%
Médio Jaguaribe	5.702.052.340	82,86%	5.052.046.877	73,41%	3.785.766.227	55,01%	2.756.340.965	37,24%	1.765.202.029	23,86%	759.459.802	10,28%	412.154.900	5,58%
Baixo Jaguaribe	24.000.000	100,00%	14.954.400	62,31%	5.296.800	22,07%	2.275.200	9,48%	580.800	2,42%	0	0,00%	425.416	1,77%
Acaraú	1.609.858.592	91,63%	1.307.498.015	74,42%	823.977.604	46,92%	560.908.880	26,08%	253.238.297	14,45%	194.663.197	11,30%	463.111.481	26,91%
Coreaú	290.507.413	97,78%	214.380.144	72,16%	130.511.637	43,93%	94.890.546	31,94%	113.000.426	36,61%	141.129.848	45,72%	249.499.940	80,83%
Curu	791.277.084	74,20%	561.324.008	52,64%	227.228.125	22,25%	77.629.820	7,57%	51.204.858	4,98%	31.755.471	3,08%	141.168.374	13,68%
Sertões de Crateús	327.759.460	69,47%	221.651.640	46,98%	83.414.240	17,68%	16.020.489	3,56%	23.020.500	5,15%	22.012.149	4,91%	7.638.852	1,70%
Metropolitanas	1.178.046.771	85,03%	857.197.795	61,87%	500.857.802	36,14%	426.818.050	30,84%	436.411.618	31,82%	293.726.731	21,39%	461.786.189	33,67%
Litoral	98.290.000	100,00%	68.308.159	70,37%	58.071.076	35,60%	51.653.756	23,94%	93.518.051	43,47%	94.874.612	44,10%	126.534.227	60,00%
Serra da Ibiapaba	136.760.152	100,00%	121.894.323	89,13%	90.781.388	66,38%	60.215.495	44,03%	35.475.600	25,16%	29.871.946	21,19%	38.773.956	27,50%
Ceará	**15.497.720.251**	**85,15%**	**12.917.353.904**	71,12%	**8.859.083.232**	48,58%	**6.118.749.473**	32,50%	3.913.719.983	20,95%	2.301.369.656	12,34%	2.345.220.893	12,58%
LEGENDA	**15.497.720.251**	**85,15%**	**12.917.353.904**	**71,12%**	**8.859.083.232**	**48,58%**	**6.118.749.473**	**32,50%**	**3.913.719.983**	**20,95%**	**2.301.369.656**	**12,34%**	**2.345.220.893**	**12,58%**

	2018		2019		2020		2021		2022		2023		2024	
	m³	%	m³	%	m³	%	m³	%	m³	%	m³	%	m³	%
Alto Jaguaribe	292.390.425	10,52%	276.007.910	9,96%	969.441.107	35,01%	958.094.353	34,64%	1.389.423.393	50,23%	1.806.478.320	65,24%	1.946.084.396	70,94%
Salgado	129.632.262	28,66%	113.284.559	25,05%	197.445.493	43,65%	243.555.161	54,43%	272.836.178	60,95%	305.804.828	68,31%	322.110.381	71,95%
Banabuiú	278.232.437	10,10%	262.524.535	9,53%	333.857.190	12,42%	252.730.869	9,42%	315.211.101	11,79%	1.114.132.995	41,64%	1.212.739.098	45,32%
Médio Jaguaribe	622.476.114	8,43%	412.236.587	5,59%	1.149.722.593	15,59%	990.976.964	13,44%	990.976.964	23,75%	2.314.790.149	31,40%	2.750.025.034	37,30%
Baixo Jaguaribe	15.002.271	62,51%	24.000.000	100,00%	15.650.046	65,21%	9.375.306	38,21%	25.050.893	100,00%	25.050.893	100,00%	25.050.893	100,00%
Acaraú	635.864.064	37,02%	1.128.868.049	65,67%	1.571.254.003	91,42%	1.348.163.484	78,44%	1.461.895.877	85,64%	1.596.708.323	93,54%	1.657.468.476	96,35%
Coreaú	279.760.662	92,16%	296.517.350	98,35%	298.359.676	98,96%	280.110.280	93,61%	284.534.970	95,08%	285.749.162	97,78%	291.717.380	99,82%
Curu	170.446.322	16,57%	270.160.950	26,26%	320.099.424	31,11%	224.921.668	21,86%	237.872.259	22,52%	396.451.869	37,62%	759.512.399	72,10%
Sertões de Crateús	56.995.468	13,07%	51.546.656	11,82%	206.911.174	47,45%	143.127.223	32,82%	89.066.096	21,62%	129.733.493	33,49%	96.787.138	54,25%
Metropolitanas	486.808.945	35,22%	860.415.614	62,25%	1.021.820.299	73,90%	856.856.730	61,92%	1.222.161.917	84,23%	1.210.822.370	82,94%	1.242.975.662	85,14%
Litoral	176.539.670	82,15%	195.253.431	90,86%	214.278.371	99,71%	176.839.059	82,95%	160.123.508	77,71%	178.741.002	98,57%	181.351.402	100,00%
Serra da Ibiapaba	55.715.144	39,51%	104.059.768	73,80%	119.307.976	84,62%	98.190.184	69,97%	88.634.871	63,16%	101.944.496	72,65%	111.671.865	79,58%
Ceará	3.183.310.543	17,10%	3.987.419.677	21,44%	6.395.573.693	34,51%	5.527.000.259	29,90%	7.285.302.602	39,25%	9.448.424.602	51,04%	10.570.214.427	57,15%
LEGENDA	**3.183.310.543**	**17,10%**	**3.987.419.677**	**21,44%**	**6.395.573.693**	**34,51%**	**5.527.000.259**	**29,90%**	**7.285.302.602**	**39,25%**	**9.448.424.602**	**51,04%**	**10.570.214.427**	**57,15%**

COMPANHIA DE GESTÃO DOS RECURSOS HÍDRICOS
DIRETORIA DE OPERAÇÕES
GERÊNCIA DE MONITORAMENTO QUANTITATIVO E QUALITATIVO

CEARÁ
GOVERNO DO ESTADO
SECRETARIA DOS RECURSOS HÍDRICOS

PROGRAMA DE GERENCIAMENTO DAS ÁGUAS TERRITORIAIS

CONVÊNIO: COGERH / DNOCS

06/08/25 - 11:10h

Bacia hidrográfica / Açude	Município		Capacidade (m³)	Cota (m)					Volume (m³)				Volume (%)				Aporte (Atual)*
				Sangria	Ano passado (06/08/2024)	Final da estação chuvosa 2024	Início do ano de 2025	Atual (06/08/2025)	Ano passado (06/08/2024)	Final da estação chuvosa 2024	Início do ano de 2025	Atual (06/08/2025)	Ano passado (06/08/2024)	Final da estação chuvosa 2024	Início do ano de 2025	Atual (06/08/2025)	
Alto Jaguaribe																	
Arneiroz II	E	Arneiroz	178.126.000	368,00	366,05	366,44	364,49	367,42	142.919.130	149.760.899	117.825.231	167.305.243	80,23%	84,08%	66,15%	93,93%	76.993.401
Benguê	E	Aiuaba	22.293.891	448,54	448,05	448,43	446,70	447,93	20.740.101	21.945.081	16.805.849	20.374.088	93,03%	98,44%	75,38%	91,39%	10.102.135
Broco	E	Tauá	11.876.302	100,00	95,77	96,13	94,68	95,26	4.146.926	4.641.947	2.815.760	3.490.006	34,92%	39,09%	23,71%	29,39%	2.176.575
Caldeirões	E	Saboeiro	1.243.681	100,00	99,71	100,03	99,89	99,72	1.120.708	1.243.681	1.197.036	1.124.949	90,11%	100,00%	96,25%	90,45%	239.937.601
Canoas	E	Assaré	60.636.405	393,00	387,64	388,15	386,16	387,53	31.796.509	34.116.572	25.514.720	31.306.357	52,44%	56,26%	42,08%	51,63%	11.258.711
Do Coronel	E	Antonina do	1.660.000	334,00	333,20	333,79	331,99	333,02	1.292.458	1.563.520	829.497	1.209.761	77,86%	94,19%	49,97%	72,88%	909.949
Facundo	E	Parambu	1.750.000	100,00	92,53	92,93	91,05	92,72	169.551	208.231	59.400	187.924	9,69%	11,90%	3,39%	10,74%	294.793
Faé	E	Quixelô	12.786.744	241,17	239,32	239,68	237,62	238,03	9.181.514	9.832.016	6.363.804	6.983.366	71,80%	76,89%	49,77%	54,61%	2.214.213
Favelas	D	Tauá	30.100.000	436,00	425,28	425,74	424,98	428,50	234.604	381.920	0	2.459.980	0,78%	1,27%	0,00%	8,17%	3.411.971
Forquilha II	D	Tauá	2.367.200	98,00	96,37	96,73	95,21	95,21	1.154.635	1.389.337	713.801	713.801	48,78%	58,69%	30,15%	30,15%	553.187
João Luís	E	Araripe	6.584.470	100,00	94,06	94,54	92,71	92,80	2.185.863	2.422.246	1.598.195	1.633.304	33,20%	36,79%	24,27%	24,81%	690.273
Mamoeiro	E	Antonina do	18.741.406	355,00	354,48	354,89	353,09	353,75	17.013.399	18.375.866	12.980.968	14.727.693	90,78%	98,05%	69,26%	78,58%	5.477.792
Monte Belo		Araripe	3.964.000	100,00	96,24	96,60	95,24	95,12	1.898.520	2.095.800	1.365.485	1.301.242	47,89%	52,87%	34,45%	32,83%	657.539
Muquém	E	Cariús	46.550.000	267,00	266,62	266,97	264,66	266,67	44.726.000	46.406.000	35.839.000	44.966.000	96,08%	99,69%	76,99%	96,60%	17.441.551
Orós	D	Orós	1.940.000.000	199,50	197,63	198,07	196,16	199,33	1.374.511.542	1.450.494.142	1.137.574.842	1.693.610.248	70,85%	74,77%	58,64%	87,30%	1.489.985.505
Parambu	E	Parambu	9.038.330	484,50	480,34	480,70	478,97	480,57	3.748.573	4.106.537	2.530.666	3.977.273	41,47%	45,43%	28,00%	44,00%	2.833.835
Pau Preto		Potengi	3.311.242	998,09	997,54	998,00	996,37	996,96	2.826.947	3.226.505	2.064.571	2.421.574	85,37%	97,44%	62,35%	73,13%	1.224.177
Poço da Pedra	D	Campos Sales	40.289.631	542,00	533,26	533,75	531,87	531,21	4.743.053	5.667.854	2.867.088	2.240.468	11,77%	14,07%	7,12%	5,56%	1.212.475
Quincoé	D	Acopiara	4.729.384	95,00	93,58	93,98	92,09	93,77	3.334.495	3.685.581	2.139.782	3.501.261	70,51%	77,93%	45,24%	74,03%	2.278.184
Rivaldo de Carvalho	E	Catarina	20.751.601	997,50	995,27	995,68	994,16	997,04	13.386.256	14.600.038	10.413.743	19.058.332	64,51%	70,36%	50,18%	91,84%	18.457.154
Trici	D	Tauá	13.000.000	433,00	430,36	430,75	428,68	432,41	5.767.971	6.581.802	3.036.041	10.882.640	44,37%	50,63%	23,35%	83,71%	16.747.857
Trussu	D	Iguatu	255.274.173	254,00	248,68	249,07	247,59	253,38	146.515.300	153.402.087	129.039.556	241.074.115	57,40%	60,09%	50,55%	94,44%	132.070.050
Valério	E	Altaneira	1.835.869	54,00	52,28	52,93	50,54	52,43	1.423.997	1.574.809	1.053.996	1.458.800	77,57%	85,78%	57,41%	79,46%	807.513
Várzea do Boi	D	Tauá	51.910.000	109,00	102,41	102,82	101,21	102,66	3.980.600	5.071.200	1.681.300	4.645.600	7,67%	9,77%	3,24%	8,95%	7.797.080
24 açudes			**2.738.820.329**						**1.838.818.652**	**1.942.793.668**	**1.516.310.331**	**2.280.654.021**	**67,14%**	**70,94%**	**55,36%**	**83,27%**	**2.045.533.521**
Salgado																	
Atalho	D	Brejo Santo	72.552.000	425,00	414,16	415,71	411,00	412,15	26.764.926	31.631.114	18.422.784	21.241.798	36,89%	43,60%	25,39%	29,28%	0
Cachoeira	E	Aurora	34.330.000	305,00	304,55	304,90	303,56	304,54	32.618.200	33.949.600	28.852.240	32.580.160	95,01%	98,89%	84,04%	94,90%	8.712.439
Gomes	D	Mauriti	2.390.000	425,00	423,31	424,23	420,32	419,79	1.994.540	2.209.820	1.294.880	1.188.500	83,45%	92,46%	54,18%	49,73%	580.146
Jenipapeiro II	E	Baixio	41.400.000	260,00	253,59	253,92	252,31	250,99	7.451.920	8.470.960	3.833.930	1.057.156	18,00%	20,46%	9,26%	2,55%	793.103
Junco	E	Granjeiro	2.030.000	292,92	292,70	292,56	291,51	292,70	1.912.313	1.837.421	1.295.642	1.912.313	94,20%	90,51%	63,82%	94,20%	896.783
Lima Campos	D	Icó	51.173.962	175,50	174,17	174,70	172,75	173,25	36.164.582	41.807.904	23.813.869	27.831.272	70,67%	81,70%	46,54%	54,39%	19.595.625
Manoel Balbino	D	Juazeiro do	37.180.000	427,00	421,37	421,57	419,99	420,17	17.940.100	18.486.100	14.407.600	14.855.000	48,25%	49,72%	38,75%	39,95%	3.187.323
Olho d'Água	E	Várzea Alegre	19.211.028	350,00	349,14	349,74	347,40	349,40	17.741.969	18.766.894	14.914.604	18.186.103	92,35%	97,69%	77,64%	94,66%	52.524.403
Prazeres	D	Barro	32.500.000	98,00	95,27	95,61	92,69	92,75	26.421.200	27.178.267	21.837.560	21.941.000	81,30%	83,63%	67,19%	67,51%	3.168.792
Quixabinha	D	Mauriti	31.780.000	418,00	401,69	403,03	400,51	400,29	5.525.920	6.823.040	4.383.680	4.170.720	17,39%	21,47%	13,79%	13,12%	1.192.684
Rosário	E	Lavras da	47.220.000	288,00	287,36	287,93	285,16	287,90	43.149.600	46.774.800	30.174.000	46.584.000	91,38%	99,06%	63,90%	98,65%	28.973.773
São Domingos II	E	Caririaçu	2.250.000	602,26	601,12	602,15	598,94	597,48	1.911.230	2.217.000	1.363.565	1.045.558	84,94%	98,53%	60,60%	46,47%	293.135
Tatajuba	E	Icó	2.720.000	220,50	219,69	220,10	218,66	220,18	2.109.800	2.336.000	1.687.400	2.412.800	77,57%	85,88%	62,04%	88,71%	2.761.957
Thomás Osterne	D	Crato	28.780.000	441,00	438,98	439,31	437,52	438,46	22.027.000	22.901.500	18.158.000	20.649.000	76,54%	79,57%	63,09%	71,75%	6.182.757
Ubaldinho	E	Cedro	42.144.843	295,00	294,45	294,91	293,10	294,54	38.582.218	41.561.868	30.272.471	39.165.193	91,55%	98,62%	71,83%	92,93%	17.101.627
15 açudes			**447.661.833**						**282.315.519**	**306.952.288**	**214.712.226**	**254.820.572**	**63,06%**	**68,57%**	**47,96%**	**56,92%**	**145.964.547**

Apoio: Gerência da Bacia Metropolitana e Gerências Regionais das Bacias de Limoeiro do Norte, Alto Jaguaribe, Parnaíba, Acaraú/Coreaú, Curu/Litoral, Salgado e Quixeramobim

COMPANHIA DE GESTÃO DOS RECURSOS HÍDRICOS
DIRETORIA DE OPERAÇÕES
GERÊNCIA DE MONITORAMENTO QUANTITATIVO E QUALITATIVO

CEARÁ
GOVERNO DO ESTADO
SECRETARIA DOS RECURSOS HÍDRICOS

PROGRAMA DE GERENCIAMENTO DAS ÁGUAS TERRITORIAIS

CONVÊNIO: COGERH / DNOCS

06/08/25 - 11:10h

Bacia hidrográfica / Açude		Município	Capacidade (m³)	Cota (m)					Volume (m³)				Volume (%)				Aporte (Atual)*
				Sangria	Ano passado (06/08/2024)	Final da estação chuvosa 2024	Início do ano de 2025	Atual (06/08/2025)	Ano passado (06/08/2024)	Final da estação chuvosa 2024	Início do ano de 2025	Atual (06/08/2025)	Ano passado (06/08/2024)	Final da estação chuvosa 2024	Início do ano de 2025	Atual (06/08/2025)	
Banabuiú		**Açude Banabuiú com os resultados da batimetria.**															
Banabuiú	D	Banabuiú	1.534.000.000	142,50	131,69	131,91	129,51	129,49	647.310.810	657.430.810	547.030.810	546.110.810	42,20%	42,86%	35,66%	35,60%	62.077.498
Capitão Mor	E	Pedra Branca	6.000.000	97,30	93,00	93,29	91,87	94,27	2.860.000	3.039.800	2.268.900	3.663.600	47,67%	50,66%	37,82%	61,06%	2.130.574
Cedro	D	Quixadá	126.000.000	114,50	103,61	103,82	102,67	102,62	5.306.749	5.924.771	3.132.771	3.036.766	4,21%	4,70%	2,49%	2,41%	2.098.027
Cipoada	E	Morada Nova	86.090.000	103,00	97,44	97,76	96,01	96,33	27.108.000	29.412.000	18.128.700	20.007.100	31,49%	34,16%	21,06%	23,24%	8.696.986
Curral Velho	D	Morada Nova	12.170.000	84,60	84,30	84,00	84,11	84,28	10.346.000	8.522.000	9.190.800	10.224.400	85,01%	70,02%	75,52%	84,01%	0
Fogareiro	D	Quixeramobim	118.000.000	236,20	236,11	236,32	234,82	234,19	116.176.626	118.000.000	91.316.666	83.015.786	98,45%	100,00%	77,39%	70,35%	9.241.761
Jatobá		Milhã	585.449	214,00	211,33	211,96	207,22	207,23	201.703	267.987	3.072	3.162	34,45%	45,77%	0,52%	0,54%	10.606
José Barbosa Filho	E	Madalena	30.000.000	310,00	309,86	310,04	308,73	307,91	29.051.532	30.000.000	21.794.182	18.263.085	96,84%	100,00%	72,65%	60,88%	1.937.046
Monsenhor Tabosa	E	Mons. Tabosa	11.233.854	655,00	651,86	651,98	650,66	650,59	6.604.747	6.745.859	5.241.706	5.169.290	58,79%	60,05%	46,66%	46,02%	1.118.690
Patu	D	Senador Pompeu	65.103.000	130,00	128,27	128,43	126,44	125,87	51.653.106	52.897.021	39.585.600	36.223.450	79,34%	81,25%	60,80%	55,64%	4.107.142
Pedras Brancas	D	Quixadá	456.000.000	127,00	120,38	120,69	119,21	118,66	152.448.764	161.555.014	123.791.714	111.611.964	33,43%	35,43%	27,15%	24,48%	16.556.052
Pirabibu	E	Quixeramobim	74.000.000	246,00	239,64	239,81	238,52	237,88	11.204.000	11.986.000	6.608.800	4.538.000	15,14%	16,20%	8,93%	6,13%	1.826.794
Poço do Barro	D	Morada Nova	52.000.000	120,00	119,61	120,03	118,13	118,45	48.587.500	52.000.000	36.507.500	38.987.500	93,44%	100,00%	70,21%	74,98%	13.419.394
Quixeramobim	D	Quixeramobim	7.889.412	102,00	101,87	102,11	100,92	100,20	7.568.853	7.889.412	5.382.740	3.922.112	95,94%	100,00%	68,23%	49,71%	1.888.952
São José I		Boa Viagem	2.242.104	100,00	99,83	100,03	98,70	98,38	2.126.338	2.242.104	1.391.732	1.211.041	94,84%	100,00%	62,07%	54,01%	493.988
São José II	E	Piquet Carneiro	13.178.908	250,00	248,68	248,86	247,00	246,63	8.992.918	9.475.899	5.567.428	5.019.366	68,24%	71,90%	42,24%	38,09%	779.502
Serafim Dias	D	Mombaça	40.940.000	254,50	252,22	252,49	251,10	252,05	28.879.787	30.307.970	22.955.472	27.980.561	70,54%	74,03%	56,07%	68,35%	10.029.099
Trapiá II	E	Pedra Branca	18.000.000	510,00	501,01	501,17	499,55	498,81	3.911.000	4.087.000	2.708.000	2.172.200	21,73%	22,71%	15,04%	12,07%	586.927
Vieirão	E	Boa Viagem	22.426.572	101,50	100,60	101,00	99,26	98,56	18.939.219	20.398.383	14.582.298	12.685.220	84,45%	90,96%	65,02%	56,56%	1.917.335
19 açudes			**2.675.859.299**						**1.179.277.651**	**1.212.182.030**	**957.188.891**	**933.845.413**	**44,07%**	**45,30%**	**35,77%**	**34,90%**	**138.916.372**
Médio Jaguaribe																	
Adauto Bezerra	E	Pereiro	4.790.000	100,00	97,18	97,48	95,86	95,93	1.900.000	2.155.000	958.632	997.816	39,67%	44,99%	20,01%	20,83%	629.859
Canafístula	E	Iracema	11.862.551	101,00	98,30	98,30	97,17	96,49	5.596.700	5.596.700	3.758.285	2.878.766	47,18%	47,18%	31,68%	24,27%	1.239.151
Castanhão	D	Alto Santo	6.700.000.000	106,00	91,93	92,57	89,47	89,52	2.300.459.600	2.434.202.400	1.840.414.000	1.848.906.800	34,34%	36,33%	27,47%	27,60%	393.323.701
Ema	D	Iracema	10.390.000	23,50	23,32	23,53	22,22	21,76	9.943.600	10.390.000	7.496.400	6.600.400	95,70%	100,00%	72,15%	63,53%	1.602.600
Figueiredo	D	Alto Santo	497.000.000	99,00	90,57	90,74	89,30	88,64	172.110.649	177.584.649	139.476.649	126.048.649	34,63%	35,73%	28,06%	25,36%	14.201.491
Jenipapeiro	D	Dep. Irapuan	14.586.823	98,50	98,07	98,29	96,96	96,52	13.366.850	13.991.021	10.217.621	8.969.278	91,64%	95,92%	70,05%	61,49%	1.942.213
Joaquim Távora	D	Jaguaribe	26.772.800	114,45	109,67	109,66	109,72	110,39	8.163.800	8.142.400	8.270.800	10.114.100	30,49%	30,41%	30,89%	37,78%	5.196.307
Madeiro	E	Pereiro	2.810.000	93,00	83,17	83,55	82,12	81,44	81.900	108.500	34.800	18.576	2,91%	3,86%	1,24%	0,66%	17.338
Nova Floresta	D	Jaguaribe	5.194.457	111,00	108,02	108,34	106,87	106,44	2.116.073	2.383.810	1.273.716	1.001.093	40,74%	45,89%	24,52%	19,27%	466.394
Potiretama	E	Potiretama	6.380.000	99,00	96,07	96,39	94,91	94,15	2.473.500	2.809.500	1.580.950	1.166.750	38,77%	44,04%	24,78%	18,29%	366.743
Riacho da Serra	E	Alto Santo	23.247.502	88,00	86,83	86,99	85,52	85,28	18.895.102	19.490.302	14.437.102	13.751.902	81,28%	83,84%	62,10%	59,15%	3.304.994
Riacho do Sangue	D	Solonópole	58.434.157	118,00	117,67	117,98	116,22	115,65	63.872.355	67.247.448	48.748.265	43.499.944	109,31%	115,08%	83,42%	74,44%	7.727.830
Santa Maria	E	Ererê	6.720.000	99,00	96,89	97,18	95,66	95,36	3.154.582	3.543.258	1.962.162	1.751.862	46,94%	52,73%	29,20%	26,07%	842.176
Santo Antônio	E	Iracema	1.191.395	54,50	52,37	52,52	51,30	51,02	685.772	717.097	479.682	434.630	57,56%	60,19%	40,26%	36,48%	182.198
Tigre	E	Solonópole	3.510.000	100,00	96,11	96,35	95,08	94,71	1.558.070	1.662.950	1.180.640	1.068.770	44,39%	47,38%	33,64%	30,45%	236.131
15 açudes			**7.372.889.685**						**2.604.378.552**	**2.750.025.034**	**2.080.289.704**	**2.067.209.337**	**35,32%**	**37,30%**	**28,22%**	**28,04%**	**431.279.126**

Apoio: Gerência da Bacia Metropolitana e Gerências Regionais das Bacias de Limoeiro do Norte, Alto Jaguaribe, Parnaíba, Acaraú/Coreaú, Curu/Litoral, Salgado e Quixeramobim

COMPANHIA DE GESTÃO DOS RECURSOS HÍDRICOS
DIRETORIA DE OPERAÇÕES
GERÊNCIA DE MONITORAMENTO QUANTITATIVO E QUALITATIVO

CEARÁ
GOVERNO DO ESTADO
SECRETARIA DOS RECURSOS HÍDRICOS

PROGRAMA DE GERENCIAMENTO DAS ÁGUAS TERRITORIAIS

CONVÊNIO: COGERH / DNOCS

06/08/25 - 11:10h

Bacia hidrográfica / Açude		Município	Capacidade (m³)	Cota (m)					Volume (m³)				Volume (%)				Aporte (Atual)*
				Sangria	Ano passado (06/08/2024)	Final da estação chuvosa 2024	Início do ano de 2025	Atual (06/08/2025)	Ano passado (06/08/2024)	Final da estação chuvosa 2024	Início do ano de 2025	Atual (06/08/2025)	Ano passado (06/08/2024)	Final da estação chuvosa 2024	Início do ano de 2025	Atual (06/08/2025)	
Baixo Jaguaribe																	
Santo Antônio de	D	Russas	25.050.893	109,28	108,98	109,31	107,70	107,60	23.153.017	25.050.893	15.429.486	14.874.420	92,42%	100,00%	61,59%	59,38%	7.332.534
1 açudes			**25.050.893**						**23.153.017**	25.050.893	**15.429.486**	14.874.420	**92,42%**	100,00%	**61,59%**	59,38%	**7.332.534**
Acaraú																	
Acaraú Mirim	D	Massapê	36.715.658	115,00	114,80	115,14	113,39	114,84	35.523.200	36.715.658	27.243.186	35.761.691	96,75%	100,00%	74,20%	97,40%	62.608.746
Araras	D	Varjota	859.533.000	153,00	152,62	153,02	150,72	151,63	821.105.500	859.533.000	658.615.320	730.260.250	95,53%	100,00%	76,62%	84,96%	194.745.055
Arrebita	E	Forquilha	18.530.000	112,00	111,81	112,24	110,71	111,79	17.797.930	18.530.000	13.714.200	17.720.870	96,05%	100,00%	74,01%	95,63%	153.665.821
Ayres de Sousa	D	Sobral	96.800.000	95,00	93,56	94,30	91,44	92,50	82.564.000	89.820.000	62.784.000	72.200.000	85,29%	92,79%	64,86%	74,59%	33.664.642
Bonito	D	Ipú	4.809.673	104,50	99,26	99,28	98,23	100,67	699.421	707.371	375.758	1.353.887	14,54%	14,71%	7,81%	28,15%	1.361.309
Carão	D	Tamboril	18.862.129	96,00	94,82	95,29	93,74	94,92	15.209.852	16.613.555	12.105.569	15.501.918	80,64%	88,08%	64,18%	82,19%	7.203.167
Carmina	E	Catunda	13.187.177	280,00	279,60	279,97	278,46	279,57	11.853.197	13.087.129	8.578.502	11.753.149	89,88%	99,24%	65,05%	89,13%	10.300.782
Edson Queiroz	D	Santa Quitéria	253.247.145	201,00	200,48	200,94	198,84	199,41	239.670.236	251.680.579	199.672.359	213.007.396	94,64%	99,38%	78,84%	84,11%	47.763.743
Farias de Sousa	D	Nova Russas	12.230.000	98,00	92,01	92,59	90,40	90,66	3.340.749	3.932.349	2.044.549	2.229.149	27,32%	32,15%	16,72%	18,23%	1.991.976
Forquilha	D	Forquilha	50.130.000	112,00	111,75	112,08	110,53	111,77	47.640.000	50.130.000	36.532.200	47.839.200	95,03%	100,00%	72,87%	95,43%	58.499.958
Jatobá II	E	Ipueiras	6.240.000	266,00	265,63	266,04	264,35	264,83	5.770.100	6.240.000	4.273.850	4.787.930	92,47%	100,00%	68,49%	76,73%	1.977.922
Jenipapo	E	Meruoca	4.939.000	634,00	633,95	634,14	631,73	634,07	4.920.104	4.939.000	4.086.617	4.939.000	99,62%	100,00%	82,74%	100,00%	74.909.298
São Vicente	D	Santana do	9.840.000	102,00	101,75	102,02	100,67	101,62	9.430.000	9.840.000	7.804.000	9.216.800	95,83%	100,00%	79,31%	93,67%	16.148.148
Sobral	D	Sobral	4.272.502	99,00	98,90	99,08	97,64	98,86	4.196.002	4.272.502	3.259.102	4.165.402	98,21%	100,00%	76,28%	97,49%	12.199.022
Taquara	D	Cariré	330.959.580	133,00	131,71	132,01	130,64	132,10	278.137.171	289.793.904	238.064.989	293.484.535	84,04%	87,56%	71,93%	88,68%	98.924.656
15 açudes			**1.720.295.864**						**1.577.857.462**	**1.655.835.047**	**1.279.154.201**	**1.464.221.177**	**91,72%**	**96,25%**	**74,36%**	**85,11%**	**775.964.244**
Coreaú																	
Angicos	E	Coreaú	49.045.419	105,50	105,18	105,51	103,62	105,04	46.075.710	49.045.419	32.957.196	44.776.462	93,94%	100,00%	67,20%	91,30%	33.972.809
Diamante		Coreaú	13.045.010	98,00	97,88	98,22	96,88	97,29	12.748.473	13.045.010	10.330.374	11.290.497	97,73%	100,00%	79,19%	86,55%	3.770.274
Diamantino II	E	Marco	18.040.000	57,00	56,83	57,09	55,66	56,83	17.227.740	18.040.000	11.946.540	17.227.740	95,50%	100,00%	66,22%	95,50%	52.504.377
Gangorra	E	Granja	54.400.000	38,00	37,67	38,02	36,42	37,74	50.374.000	54.400.000	36.110.000	51.228.000	92,60%	100,00%	66,38%	94,17%	35.207.287
Itaúna	E	Granja	72.396.177	32,50	32,37	32,62	31,18	32,28	70.083.095	72.396.177	50.850.148	68.481.730	96,80%	100,00%	70,24%	94,59%	91.156.037
Martinópole		Martinópole	24.830.000	99,00	98,65	98,96	97,49	97,53	22.635.500	24.579.200	15.902.900	16.111.300	91,16%	98,99%	64,05%	64,89%	5.938.899
Premuoca	D	Uruoca	5.200.000	88,00	87,62	88,08	86,54	86,84	4.732.600	5.200.000	3.491.600	3.803.600	91,01%	100,00%	67,15%	73,15%	1.715.445
Trapiá III		Coreaú	3.411.743	100,00	98,69	99,11	97,46	98,80	2.417.839	2.712.160	1.656.297	2.492.063	70,87%	79,49%	48,55%	73,04%	1.789.807
Tucunduba	D	Senador Sá	39.370.585	109,00	109,00	109,38	107,77	108,95	39.370.585	39.370.585	27.059.516	38.855.402	100,00%	100,00%	68,73%	98,69%	278.588.829
Várzea da Volta	D	Moraújo	12.500.000	108,00	107,79	108,04	106,45	107,79	11.502.500	12.500.000	6.210.000	11.502.500	92,02%	100,00%	49,68%	92,02%	24.481.657
10 açudes			**292.238.934**						**277.168.041**	**291.288.551**	**196.514.571**	**265.769.294**	**94,84%**	**99,67%**	**67,24%**	**90,94%**	**529.125.420**

Apoio: Gerência da Bacia Metropolitana e Gerências Regionais das Bacias de Limoeiro do Norte, Alto Jaguaribe, Parnaíba, Acaraú/Coreaú, Curu/Litoral, Salgado e Quixeramobim

COMPANHIA DE GESTÃO DOS RECURSOS HÍDRICOS
DIRETORIA DE OPERAÇÕES
GERÊNCIA DE MONITORAMENTO QUANTITATIVO E QUALITATIVO

CEARÁ
GOVERNO DO ESTADO
SECRETARIA DOS RECURSOS HÍDRICOS

PROGRAMA DE GERENCIAMENTO DAS ÁGUAS TERRITORIAIS

CONVÊNIO: COGERH / DNOCS

06/08/25 - 11:10h

Bacia hidrográfica / Açude		Município	Capacidade (m³)	Cota (m)					Volume (m³)				Volume (%)				Aporte (Atual)*
				Sangria	Ano passado (06/08/2024)	Final da estação chuvosa 2024	Início do ano de 2025	Atual (06/08/2025)	Ano passado (06/08/2024)	Final da estação chuvosa 2024	Início do ano de 2025	Atual (06/08/2025)	Ano passado (06/08/2024)	Final da estação chuvosa 2024	Início do ano de 2025	Atual (06/08/2025)	
Curu																	
Caxitoré	D	Umirim	202.000.000	73,00	72,72	73,10	71,41	72,80	194.998.880	202.000.000	165.196.000	196.999.200	96,53%	100,00%	81,78%	97,52%	99.039.251
Desterro	E	Caridade	4.568.870	999,10	998,76	999,16	997,67	998,66	4.041.281	4.568.870	2.547.201	3.893.167	88,45%	100,00%	55,75%	85,21%	2.975.479
Escuridão		Canindé	2.720.000	108,50	105,81	106,05	104,95	104,39	1.418.600	1.506.650	1.111.432	963.893	52,15%	55,39%	40,86%	35,44%	153.980
Frios	D	Umirim	33.020.000	50,00	49,81	50,23	48,44	49,84	31.937.000	33.020.000	24.542.400	32.108.000	96,72%	100,00%	74,33%	97,24%	167.844.266
General Sampaio	D	General Sampaio	322.200.000	124,50	118,71	119,14	117,21	118,01	166.442.520	174.531.680	138.224.520	153.274.120	51,66%	54,17%	42,90%	47,57%	37.675.056
Itapajé	E	Itapajé	3.914.316	278,00	278,01	278,09	276,22	277,86	3.914.316	3.914.316	2.958.854	3.836.287	100,00%	100,00%	75,59%	98,01%	6.924.378
Jerimum	E	Irauçuba	18.750.345	147,00	146,62	147,01	145,43	146,52	17.880.425	18.750.345	15.253.971	17.651.499	95,36%	100,00%	81,35%	94,14%	14.364.586
Melancia	E	São Luis do Curu	27.364.055	48,00				46,61	21.662.109	22.932.997	17.301.705	21.081.011	79,16%	83,81%	63,23%	77,04%	7.453.990
Pentecoste	D	Pentecoste	360.000.000	58,00	55,47	55,74	54,33	55,78	242.169.111	253.540.417	197.935.614	255.232.761	67,27%	70,43%	54,98%	70,90%	98.140.804
Salão	D	Canindé	6.040.000	95,00	90,53	90,95	89,39	88,97	1.528.000	1.780.000	923.300	729.800	25,30%	29,47%	15,29%	12,08%	334.088
São Domingos		Caridade	3.980.287	98,50	97,95	98,42	96,61	96,74	3.479.287	3.906.740	2.419.425	2.505.076	87,41%	98,15%	60,79%	62,94%	1.144.401
São Mateus	D	Canindé	10.330.000	191,00	190,46	190,96	188,78	188,55	9.250.000	10.250.000	6.264.400	5.924.000	89,55%	99,23%	60,64%	57,35%	2.339.297
Sousa	E	Canindé	30.840.000	162,50	151,28	151,87	149,02	148,03	609.143	1.713.137	121.300	36.520	1,98%	5,55%	0,39%	0,12%	58.855
Tejuçuoca	D	Tejuçuoca	27.638.231	116,61	116,12	116,49	114,76	116,02	25.429.215	27.097.247	20.045.431	24.978.395	92,01%	98,04%	72,53%	90,38%	11.904.933
14 acudes			**1.053.366.104**						**724.759.886**	**759.512.399**	**594.845.553**	**719.213.727**	**68,80%**	**72,10%**	**56,47%**	**68,28%**	**450.353.364**
Sertões de Crateús																	
Barra Velha	E	Independência	99.560.000	333,60	323,72	324,26	321,88	323,71	1.083.776	2.010.242	10.560	1.072.293	1,09%	2,02%	0,01%	1,08%	3.448.288
Carnaubal	E	Crateús	46.621.015	300,00	296,81	297,30	295,46	295,20	20.650.944	23.432.653	14.311.678	13.204.310	44,30%	50,26%	30,70%	28,32%	4.711.238
Colina	E	Quiterianópolis	4.297.203	98,00	94,98	95,42	93,56	97,34	1.183.882	1.529.267	483.217	3.472.487	27,55%	35,59%	11,24%	80,81%	9.681.512
Cupim	E	Independência	4.604.394	98,00	94,22	94,68	92,88	95,94	726.150	974.792	185.983	1.915.194	15,77%	21,17%	4,04%	41,59%	3.099.613
Do Batalhão	E	Crateús	2.773.772	276,80	276,33	276,79	274,88	276,03	2.289.123	2.763.460	1.119.003	1.979.772	82,53%	99,63%	40,34%	71,37%	277.708.362
Flor do Campo	E	Novo Oriente	107.598.366	351,00	342,17	342,60	340,89	341,39	11.890.260	14.046.770	6.655.950	8.575.820	11,05%	13,05%	6,19%	7,97%	7.090.430
Jaburu II	E	Independência	75.310.431	314,50	309,61	309,95	308,35	309,08	15.808.746	18.113.515	8.373.591	12.216.017	20,99%	24,05%	11,12%	16,22%	12.224.375
Realejo	D	Crateús	31.468.087	327,00	322,29	322,71	320,87	321,38	12.822.829	14.135.830	8.868.801	10.205.793	40,75%	44,92%	28,18%	32,43%	4.356.000
São José III	E	Ipaporanga	9.121.758	100,00	99,68	100,03	98,58	99,63	8.403.026	9.121.758	6.097.393	8.290.724	92,12%	100,00%	66,84%	90,89%	6.315.626
Sucesso	E	Tamboril	7.126.851	100,00	99,56	99,93	98,40	99,61	6.126.843	6.967.759	3.915.257	6.240.480	85,97%	97,77%	54,94%	87,56%	60.545.074
10 acudes			**388.481.877**						**80.985.577**	**93.096.046**	**50.021.433**	**67.172.890**	**20,85%**	**23,96%**	**12,88%**	**17,29%**	**389.180.517**
Metropolitanas																	
Acarape do Meio	E	Redenção	29.276.260	130,02	129,80	130,31	125,87	129,74	28.763.862	29.276.260	20.273.112	28.624.397	98,25%	100,00%	69,25%	97,77%	39.202.894
Amanary	D	Maranguape	9.343.629	96,00	95,71	96,16	94,58	95,74	8.602.622	9.343.629	5.958.838	8.677.092	92,07%	100,00%	63,77%	92,87%	15.452.493
Amarelas	E	Beberibe	47.679.378	23,00				13,66	4.557.426	5.132.079	2.306.999	2.778.297	9,56%	10,76%	4,84%	5,83%	3.232.836
Aracoiaba	E	Aracoiaba	163.423.760	95,00	95,01	95,38	93,90	95,00	163.423.760	163.423.760	144.323.552	163.423.760	100,00%	100,00%	88,31%	100,00%	77.694.640
Batente	E	Ocara	45.430.122	71,86	71,50	71,80	70,31	70,52	41.089.050	44.706.610	28.454.810	30.465.019	90,44%	98,41%	62,63%	67,06%	15.723.637
Castro	E	Itapiúna	62.310.000	151,50	147,22	147,39	146,07	146,26	33.062.240	33.995.880	26.746.440	27.789.920	53,06%	54,56%	42,92%	44,60%	7.065.886
Catucinzenta	E	Aquiraz	22.780.810	45,00	44,79	45,08	43,86	44,86	21.775.769	22.780.810	17.436.942	22.110.783	95,59%	100,00%	76,54%	97,06%	14.076.559
Cauhipe	E	Caucaia	10.951.259	36,89	36,63	36,95	35,57	36,77	10.081.301	10.951.259	6.777.948	10.549.740	92,06%	100,00%	61,89%	96,33%	134.751.970
Cocó	E	Fortaleza	5.095.672	14,90	9,54	12,40	9,54	11,10	23.138	1.273.957	23.138	290.265	0,45%	25,00%	0,45%	5,70%	20.199.647
Gavião	E	Pacatuba	33.448.122	36,00	35,43	35,64	35,22	35,54	30.034.715	31.292.286	28.807.854	30.693.442	89,79%	93,55%	86,13%	91,76%	0
Germinal	E	Pacoti	2.107.201	354,00	354,02	354,09	353,69	354,03	2.107.201	2.107.201	2.032.307	2.107.201	100,00%	100,00%	96,45%	100,00%	36.520.850
Itapebussu	D	Maranguape	7.082.804	117,04	116,80	117,17	115,27	116,97	6.630.067	7.082.804	4.118.529	6.949.239	93,61%	100,00%	58,15%	98,11%	54.379.807
Macacos	E	Ibaretama	13.195.355	120,00	119,75	119,97	118,71	118,88	12.650.993	13.130.032	10.468.725	10.790.658	95,87%	99,50%	79,34%	81,78%	2.719.349
Malcozinhado	E	Cascavel	38.094.707	24,00	23,83	24,13	22,77	23,88	36.887.818	38.094.707	29.632.332	37.242.785	96,83%	100,00%	77,79%	97,76%	24.695.808
Maranguapinho	E	Maranguape	9.350.000	51,50	49,57	50,97	48,35	48,46	4.573.060	7.820.600	2.491.100	2.654.560	48,91%	83,64%	26,64%	28,39%	28.149.422
Pacajus	E	Chorozinho	254.953.788	38,00	37,97	38,09	37,17	37,47	253.733.618	254.953.788	221.195.753	233.397.453	99,52%	100,00%	86,76%	91,55%	0
Pacoti	E	Horizonte	371.931.972	45,00	44,12	44,80	39,93	42,85	332.689.977	363.013.337	183.280.986	280.845.936	89,45%	97,60%	49,28%	75,51%	0
Penedo	E	Maranguape	2.227.790	998,00	996,88	997,39	994,68	997,06	1.671.637	1.920.388	820.979	1.754.088	75,04%	86,20%	36,85%	78,74%	7.223.861
Pesqueiro	E	Capistrano	10.539.083	196,65	196,71	197,03	195,42	196,74	10.539.083	10.539.083	8.692.990	10.539.083	100,00%	100,00%	82,48%	100,00%	80.279.399
Pompeu Sobrinho	D	Choró	142.371.245	218,50	207,35	207,66	206,30	206,34	13.771.206	15.268.389	9.403.995	9.556.957	9,67%	10,72%	6,61%	6,71%	4.766.466
Riachão	E	Itaitinga	49.812.148	45,00	44,10	44,77	39,91	42,85	44.433.958	48.437.722	24.584.440	37.616.146	89,20%	97,24%	49,35%	75,52%	0
Sitios Novos	E	Caucaia	127.948.163	45,15	45,29	45,94	43,99	45,11	127.948.163	127.948.163	102.531.086	126.998.953	100,00%	100,00%	80,13%	99,26%	499.670.754
Tijuquinha	E	Baturité	482.920	352,08	352,10	352,13	350,24	352,11	482.920	482.920	285.404	482.920	100,00%	100,00%	59,10%	100,00%	10.607.784
23 açudes			**1.459.836.188**						**1.189.533.583**	**1.242.975.662**	**880.648.259**	**1.086.338.695**	**81,48%**	**85,14%**	**60,33%**	**74,42%**	**1.076.414.060**

Apoio: Gerência da Bacia Metropolitana e Gerências Regionais das Bacias de Limoeiro do Norte, Alto Jaguaribe, Parnaíba, Acaraú/Coreaú, Curu/Litoral, Salgado e Quixeramobim

COMPANHIA DE GESTÃO DOS RECURSOS HÍDRICOS
DIRETORIA DE OPERAÇÕES
GERÊNCIA DE MONITORAMENTO QUANTITATIVO E QUALITATIVO

CEARÁ
GOVERNO DO ESTADO
SECRETARIA DOS RECURSOS HÍDRICOS

PROGRAMA DE GERENCIAMENTO DAS ÁGUAS TERRITORIAIS

CONVÊNIO: COGERH / DNOCS

06/08/25 - 11:10h

Bacia hidrográfica / Açude		Município	Capacidade (m³)	Cota (m)					Volume (m³)				Volume (%)				Aporte (Atual)*
				Sangria	Ano passado (06/08/2024)	Final da estação chuvosa 2024	Início do ano de 2025	Atual (06/08/2025)	Ano passado (06/08/2024)	Final da estação chuvosa 2024	Início do ano de 2025	Atual (06/08/2025)	Ano passado (06/08/2024)	Final da estação chuvosa 2024	Início do ano de 2025	Atual (06/08/2025)	
Litoral																	
Gameleira	E	Itapipoca	27.921.849	37,00	36,79	37,05	35,52	36,80	26.604.190	27.921.849	19.070.231	26.666.936	95,28%	100,00%	68,30%	95,51%	54.222.163
Gerardo Atimbone		Sobral	6.098.860	100,00	99,67	100,04	98,54	99,59	5.467.818	6.098.860	3.495.388	5.314.838	89,65%	100,00%	57,31%	87,14%	48.078.618
Missi	E	Miraíma	54.369.088	54,70	54,32	54,71	53,02	54,34	49.859.270	54.369.088	36.364.174	50.096.629	91,71%	100,00%	66,88%	92,14%	48.423.071
Mundaú	D	Uruburetama	21.300.000	166,38	166,28	166,44	163,16	166,35	21.180.250	21.300.000	17.444.050	21.264.075	99,44%	100,00%	81,90%	99,83%	32.337.998
Patos	D	Sobral	7.550.000	106,00	105,29	105,79	104,11	105,20	6.201.000	7.151.000	4.297.200	6.030.000	82,13%	94,72%	56,92%	79,87%	5.844.206
Poço Verde		Itapipoca	13.337.024	68,00	67,73	68,14	66,32	67,70	12.241.184	13.337.024	7.405.346	12.119.424	91,78%	100,00%	55,52%	90,87%	43.791.186
Quandú	E	Itapipoca	2.447.902	98,50	98,47	98,56	96,11	98,46	2.435.153	2.447.902	1.517.159	2.430.903	99,48%	100,00%	61,98%	99,31%	9.764.327
Santa Maria de	D	Sobral	8.200.000	98,00	97,59	97,98	96,52	97,57	7.347.200	8.158.400	5.140.800	7.305.600	89,60%	99,49%	62,69%	89,09%	11.447.543
Santo Antonio de Aracatiacu	D	Sobral	24.340.000	93,00	92,56	92,97	91,39	92,40	22.527.200	24.216.400	17.932.500	21.868.000	92,55%	99,49%	73,68%	89,84%	10.672.818
São Pedro Timbaúba	D	Miraíma	15.786.679	99,00	98,66	99,08	97,19	98,62	14.553.771	15.786.679	8.878.035	14.408.723	92,19%	100,00%	56,24%	91,27%	131.826.704
10 açudes			**181.351.402**						**168.417.035**	**180.787.202**	**121.544.883**	**167.505.127**	**92,87%**	**99,69%**	**67,02%**	**92,36%**	**396.408.634**
Serra da Ibiapaba																	
Jaburu I	E	Ubajara	140.325.089	716,38	713,13	713,29	710,62	713,17	108.225.123	109.715.606	86.998.110	108.597.744	77,12%	78,19%	62,00%	77,39%	31.073.850
1 açudes			**140.325.089**						**108.225.123**	**109.715.606**	**86.998.110**	**108.597.744**	**77,12%**	**78,19%**	**62,00%**	**77,39%**	**31.073.850**
157 açudes	.	.	**18.496.177.497**	.	.	.	.	.	**10.054.890.098**	**10.570.214.427**	**7.993.657.648**	**9.430.222.418**	**54,36%**	**57,15%**	**43,22%**	**50,98%**	**6,418 bilhões de m³**

Desconsiderado alterações no açude Atalho, que tem recebido águas transferidas do Rio São Francisco. Desconsiderad

* - A água liberada durante a

E - estado; D - DNOCS

Açudes para seco

Açudes em volume morto

Açudes que permanecem sangrando

Açudes que pararam de sangrar (informado hoje)

P

Açudes que não estão mais sangrando

N

Apoio: Gerência da Bacia Metropolitana e Gerências Regionais das Bacias de Limoeiro do Norte, Alto Jaguaribe, Parnaíba, Acaraú/Coreaú, Curu/Litoral, Salgado e Quiaramobim